kadaster

Agenda
KLIC bijeenkomst
6 maart 2026

6 maart 2026

Agenda

- Welkom
- Terugblik
- Ontwikkelingen
- WIBON-evaluatie / Wijziging WIBON
- Wist je dat? KLIC-viewer
- KLIC kalender 2026

kadaster

Terugblik - Statistieken

Aantal KLIC-meldingen

	2020	2021	2022	2023	2024	2025	%
Graafmelding	729.061	771.795	771.795	850.331	878.974	914.753	80%
Oriëntatieverzoek	122.584	134.684	168.792	169.122	185.316	187.325	16%
Calamiteitenmelding	39.758	41.071	40.722	42.021	42.307	41.829	4%
Totaal	**891.403**	**947.550**	**1.008.010**	**1.061.474**	**1.106.597**	**1.143.907**	**100%**

Terugblik - Statistieken

Aantal Afwijkende situatie

Totaal afwijkend situaties	2023	2024	2025
Ligging	773	1242	1265
Onbekend net	940	864	933
Niet gevonden net	237	57	NVT

kadaster

11:27

Terugblik - Statistieken

Jaar	Aantal EV	Aantal KLIC-meldingen	%
2021	470.604	947.550	50%
2022	503.311	1.008.010	50%
2023	525.867	1.061.474	56%
2024	517.800	1.106.597	47%
2025	511.509	1.143.907	45%

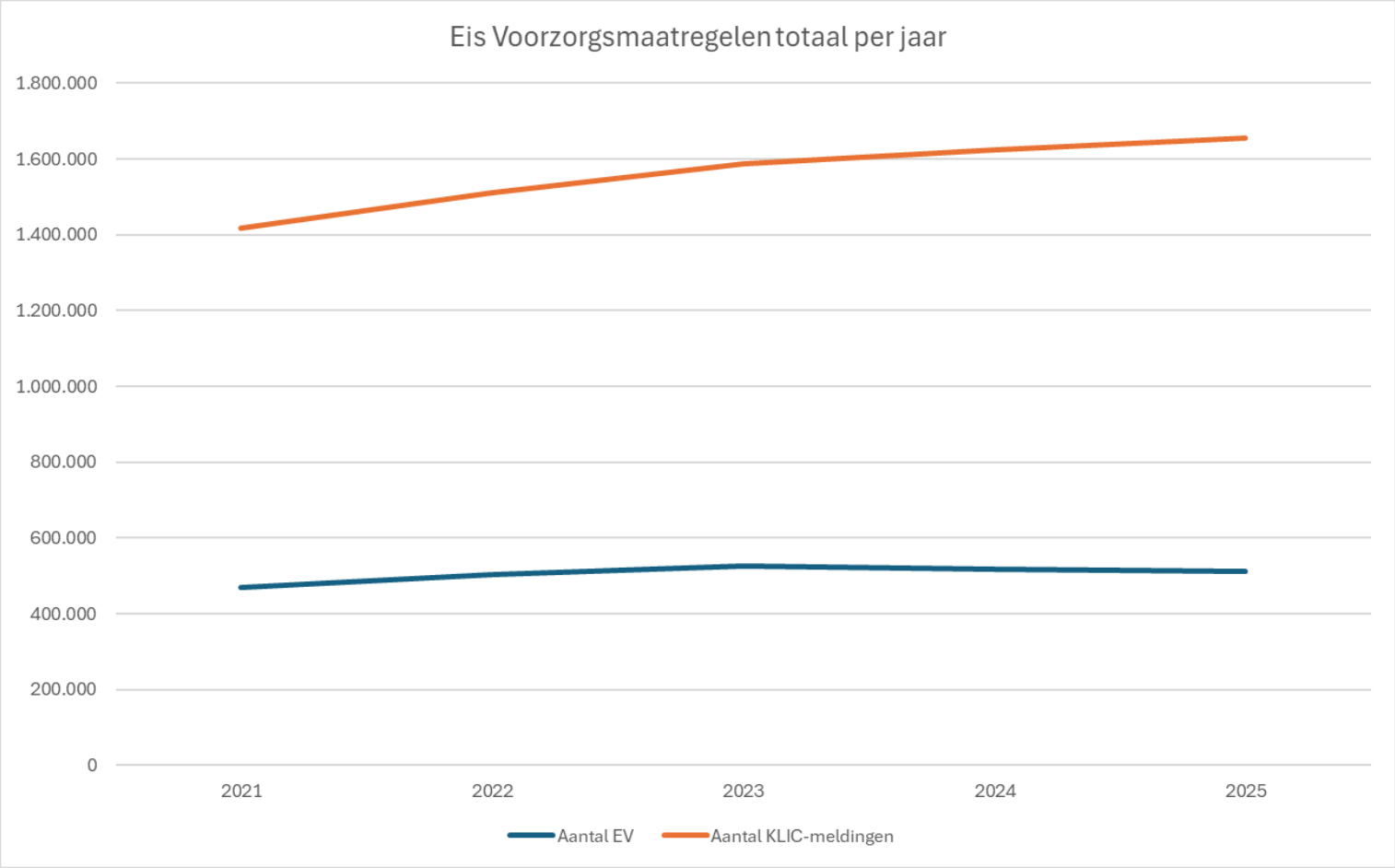

Terugblik

kadaster

11:27

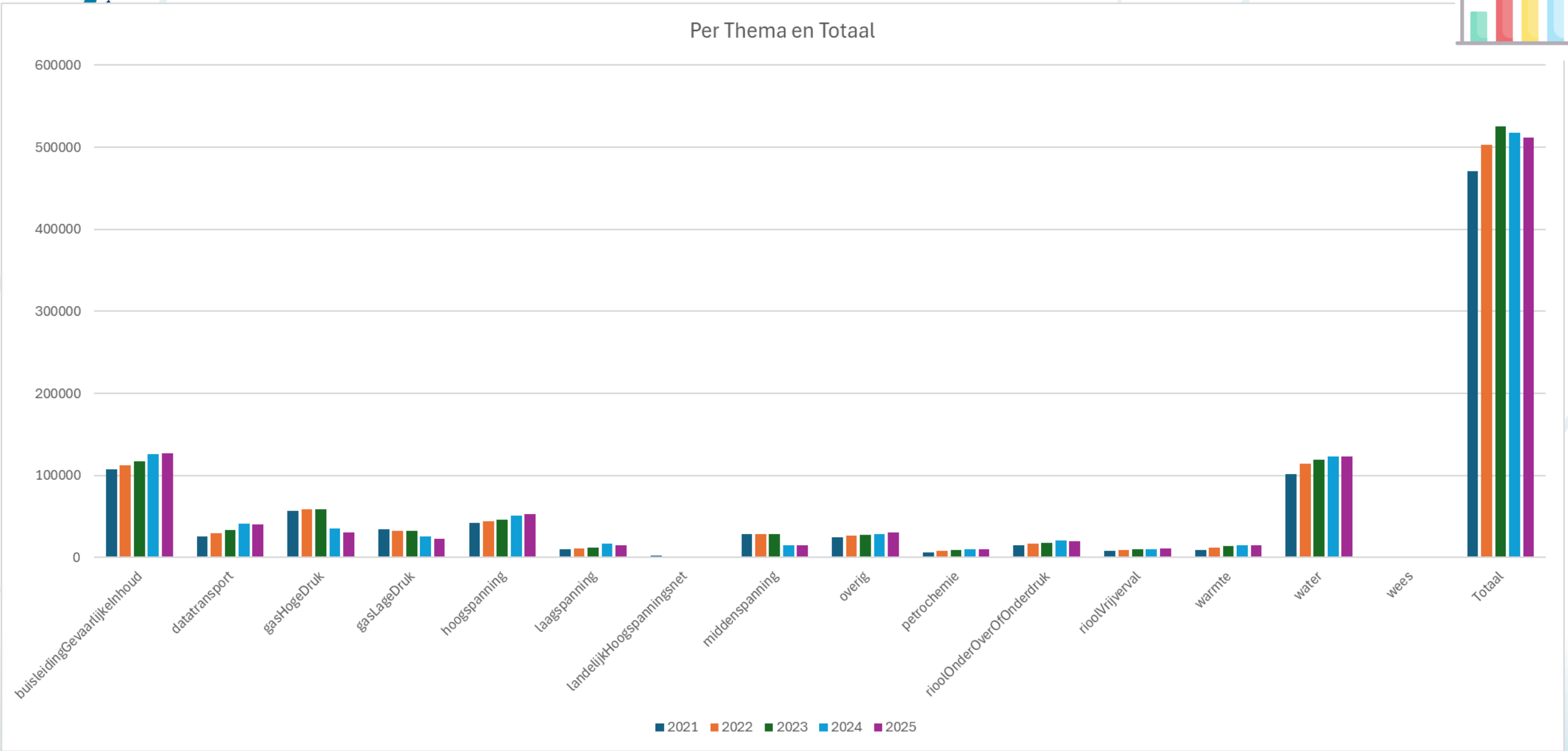

Terugblik - Schaderapportage

- Vanaf 1 januari 2026: aanleveren geen/wel schades over 2025 door in 2025 actieve netbeheerders.
- 21 januari 2026: Brief van RDI brief naar de netbeheerders die nog informatie moeten verstrekken.
- Van de 1412 netbeheerders die moeten rapporteren hebben 220 netbeheerders aangegeven dat ze schade hebben gehad.
- Aantal aangeleverde schades is nu 5% lager dan vorig jaar.
- Schaderapportage input voor infographic RDI.
- Publicatie op site Kadaster en infographic (RDI): eind maart/april 2026.

Terugblik - Aanpassingen

Release – 6 januari 2026

Voor deze release is het volgende onderwerp gepland:

Aanvragen via Mijn Kadaster:

- Vanaf 6 januari is het niet meer mogelijk om een postbusadres op te geven bij de bedrijfsgegevens van een opdrachtgever.
  (*Merk op dat via de B2B-REST-API het gebruik van postbusadressen sinds de invoering al niet meer wordt ondersteund.*)

Kijk op GitHub voor de actuele planning.

Terugblik – Technische werkzaamheden

Technisch

- Voorbereiden overgang naar nieuwe private cloud infrastructuur
- Security

Terugblik - KLIC Productplan 2025-2028

Het KLIC Productplan is geactualiseerd.

Het KLIC Productplan beschrijft de dienstverlening en de ontwikkelingen voor de periode 2025-2028. Het is een verdere uitwerking van het Meerjarenbeleidsplan van het Kadaster voor het deelgebied kabels en leidingen.

Download productplan

Terugblik – Verstoring 23 februari 2026

Het KLIC-ordersysteem heeft van zaterdagochtend 21 februari 2026 tot maandag 23 februari rond 23.00 een verstoring gehad.
De verstoring hield in dat er wel een KLIC-melding gedaan kon worden, maar er geen verdere afhandeling mogelijk was door het Kadaster.
Dat betekent dat er geen ontvangstbevestiging naar de grondroerder, geen graafberichten naar de netbeheerder en dus ook geen levering geproduceerd kon worden.

Het was wel mogelijk om een calamiteitenmelding te doen. De grondroerder kon de contactgegevens van de netbeheerders op het scherm direct overnemen en/of printen bij de calamiteitenmelding.
Let op: Bij een calamiteitenmelding is de lijst met contactgegevens minimaal vereist.

Berichtgeving over verstoringen is terug te vinden op de Kadaster Servicepagina en via Mijn Kadaster nieuwsberichten.

Storingen en onderhoud KLIC

Overzicht van alle storingen en gepland onderhoud van KLIC. Wilt u automatisch een melding ontvangen bij storing of onderhoud? Meld u dan aan voor de RSS.

Naar pagina RSS

Gemelde Storingen

Datum en tijd	Omschrijving	Status	
21-02-2026 10.46	KLIC vertraging in verzenden ontvangstbevestigingen en leveringen	✔ Verholpen	+

Gepland Onderhoud

Datum en tijd	Omschrijving	Status	
20-02-2026 18.00	Diverse diensten tijdelijk niet beschikbaar	✔ Uitgevoerd	+
13-02-2026 19.00	Diverse diensten tijdelijk niet beschikbaar	✔ Uitgevoerd	+

Ontwikkelingen - Onderwerpen Jaarplan 2026

Technisch:

- Overgang naar nieuwe private cloud infrastructuur
- Technische vernieuwing orderproces en klantregistratie
- Security

Functioneel:

- 2FA grondroerders
- Upgrade KLIC-standaarden
- Cyber Recovery Solution (CRS) en draaiboek geen KLIC informatie beschikbaar
- WCAG/Toegankelijkheid KLIC netbeheerder applicaties
- Kadaster KLIC-viewer (adaptieve aanpassingen)

Ontwikkelingen – Overige onderwerpen Jaarplan 2026

- Voorbereiding WIBON evaluatie aanpassingen
- Adaptieve aanpassingen KLIC-dienstverlening
- IMKL statistieken/rapportage
- Generieke processen: KLIC Inzien status grondroerders
- Implementatie Gigabit Infrastructure Act (GIA)
- Vernieuwen Beheren belangen

Ontwikkelingen - Onderzoek

- Werkgroep 3D (PoC en analyse standaarden)
- Werkgroep Geen KLIC en dan?
- ZoARG onderzoeken (Uni van Twente)
- TCS KLIC: Nieuwe issues KLIC-standaarden

Ontwikkelingen – 2FA grondroerders

Tweeledige verificatie (2FA) is een aanmeldingsproces waarbij twee verschillende soorten identiteitsverificatie nodig zijn om toegang te krijgen tot een account.

Het Kadaster is al geruime tijd bezig met het voorbereiden op de implementatie van 2FA voor de gebruikers die geen eHerkenning nodig hebben om in te loggen.

Ontwikkelingen – 2FA grondroerders

<u>Veiligere toegang en gebruik Mijn Kadaster</u>

- Inlogcode wordt een (uniek) e-mailadres
- Gebruik Authenticator app (zoals Google/Microsoft) bij inloggen.

Er volgt Kadaster-brede communicatie.
We verwachten bij onze volgende bijeenkomst meer uitleg te geven.

Informatie wordt altijd verzonden naar e-mailadres 1e beheerder!
Dus zorg dat de 1e beheerder actueel is.

kadaster

Ontwikkelingen - WIBON-evaluatie / Wijziging WIBON

In het kort
De Wet informatie-uitwisseling bovengrondse en ondergrondse netten en netwerken reguleert de uitwisseling van liggingsgegevens van kabels en leidingen tussen grondroerders en netbeheerders met als doel om schades aan ondergrondse kabels en leidingen te voorkomen. Naar aanleiding van een beleidsevaluatie wordt de wet gewijzigd om knelpunten op het gebied van wet en regelgeving te adresseren.

Wil je ook reageren?
Ga naar de site van de Overheid.

Einddatum consultatie
6 april 2026

Relevante documenten

- Wijzigingswet Wibon PDF
- Wijzigingswet Wibon Memorie van Toelichting PDF
- Beleidskompas Wijzigingswet Wibon PDF

Reacties op deze consultatie *7 openbaar*

Aannemersbedrijf A. Faber B.V. (Bedrijfsleider PT van der Meulen) Sondel | 25 feb 2026
Lees de volledige reactie →

Gebr Harmsen (Dhr F W Harmsen) Apeldoorn | 21 feb 2026
Lees de volledige reactie →

Smink Infra (Machinist mobiele graaf machine Bryan Van Middelaar) Nijkerk | 21 feb 2026
Lees de volledige reactie →

Ontwikkelingen - Planning upgrade KLIC-standaarden

De oplevering van versie 3 in de ETO is vertraagd. Oorzaak van de vertraging is dat we te maken hebben met een groot Kadaster breed technisch datamigratie (datacenter) traject, waar alle prioriteit op zit en veel resources naar toe gaan.

Aandachtspunt: Samenloop WIBON-evaluatie en upgrade KLIC-standaarden.

- Er is een consultatie van de WIBON naar aanleiding van een evaluatie van de wet- en regelgeving, die mogelijk gevolgen heeft voor de informatievoorziening.
- Tegelijkertijd staat een programma voor de upgrade KLIC-standaarden gepland, maar de start daarvan is afhankelijk van lopende technische trajecten.
- Bij de verdere uitwerking wordt zorgvuldig gekeken naar de uitkomsten van de evaluatie, zodat ontwikkelingen goed op elkaar aansluiten.

Dit is op verzoek van het KGO KLIC (KLIC Gebruikersoverleg).

INFRA Relatiedagen 2026

Op 10, 11 & 12 februari 2026 heeft het Kadaster als exposant deelgenomen aan de INFRA Relatiedagen in Hardenberg.

kadaster

11:28

Wist je dat? KLIC-viewer

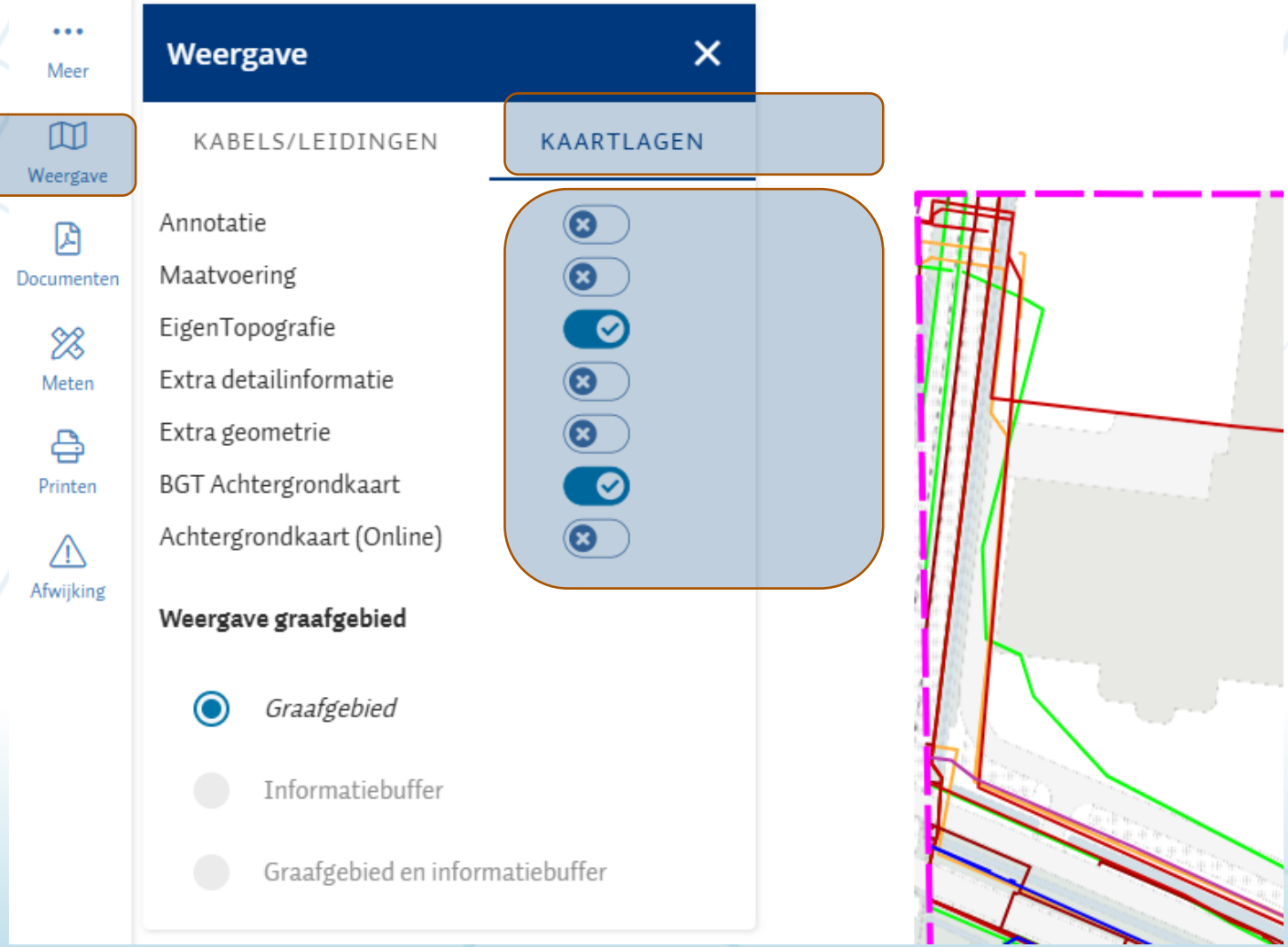

Annotatie

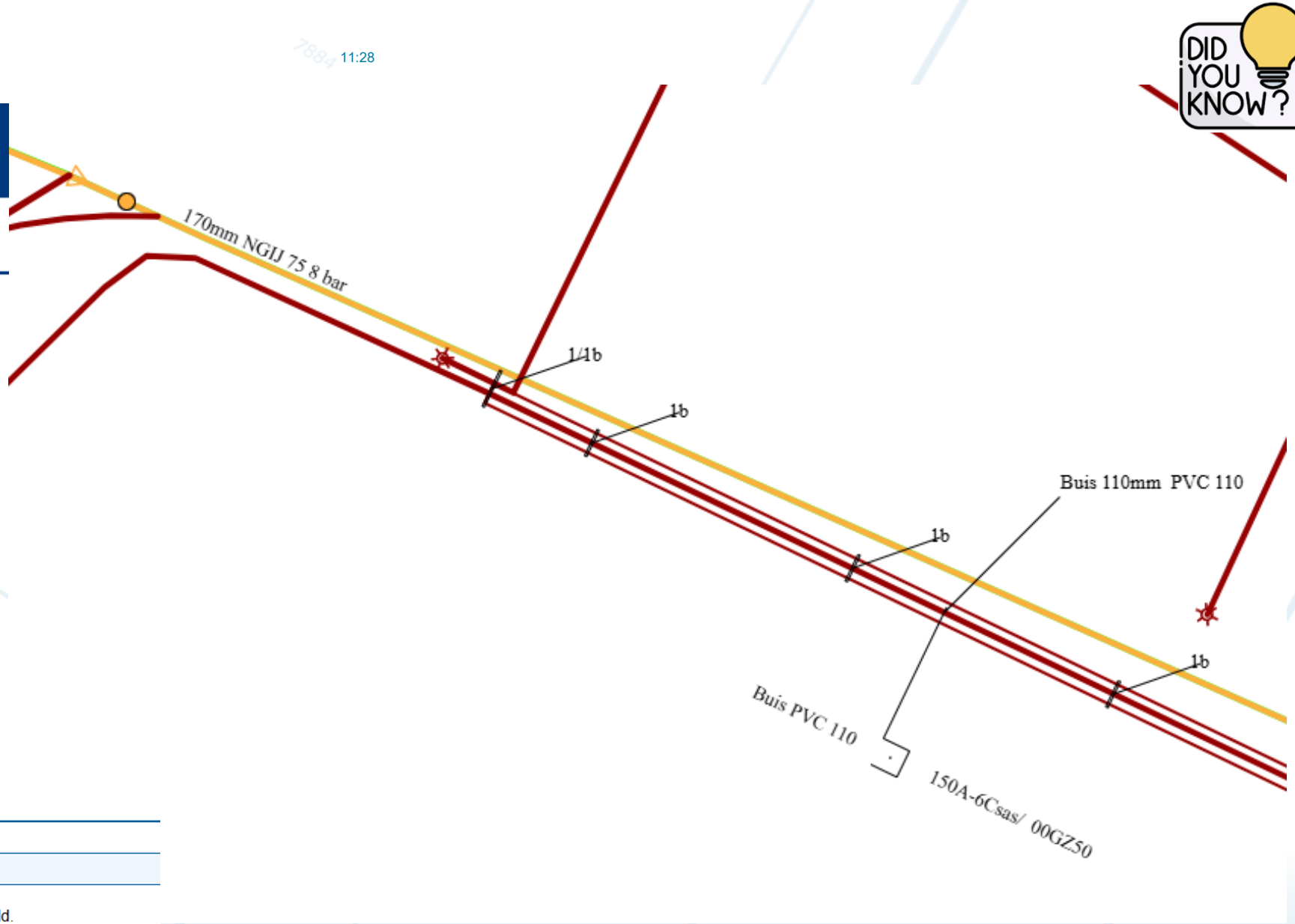

Naam	Annotatie
Alias	annotatie
Definitie	Teksten en symbolen weergegeven in het kaartbeeld.
Toelichting	Annotatie kan worden gebruikt om informatie toe te voegen aan het kaartbeeld. Via het attribuut “label” kan tekst of numerieke waarde worden doorgegeven.

Maatvoering



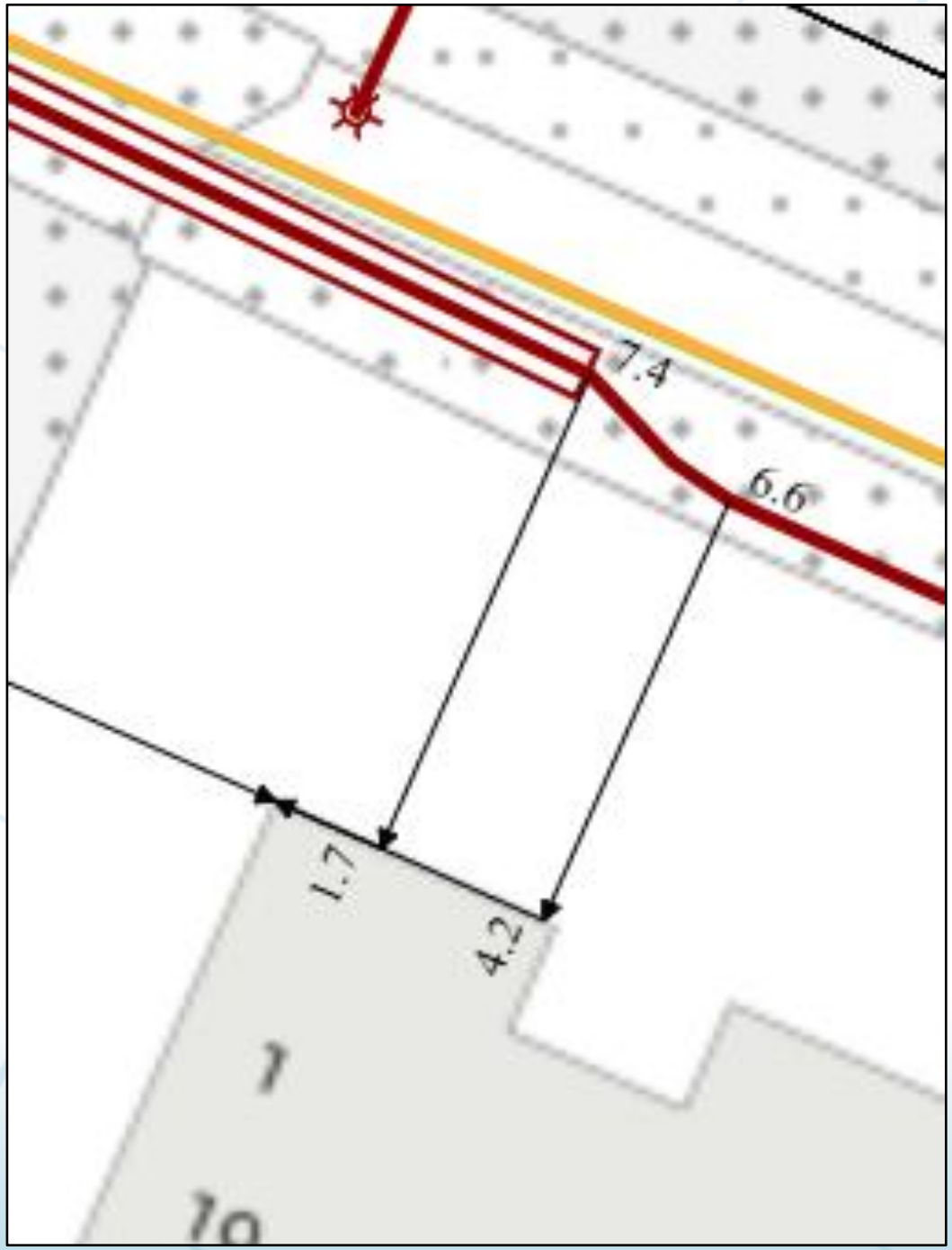

Naam	Maatvoering
Alias	maatvoering
Definitie	Teksten en symbolen in het kaartbeeld diegebruikt worden om de positie van een netwerkelement ten opzichte van objecten weer te geven.
Toelichting	Voor de aanduiding van de relatieve positie van een leiding of leidingelement ten opzichte van een ander object. Via het “annotatieType” attribuut kan het soort annotatie of maatvoering object worden bepaald – voor visualisatie - en via het attribuut “label” kan de tekst of numerieke waarde worden doorgegeven.

EigenTopografie

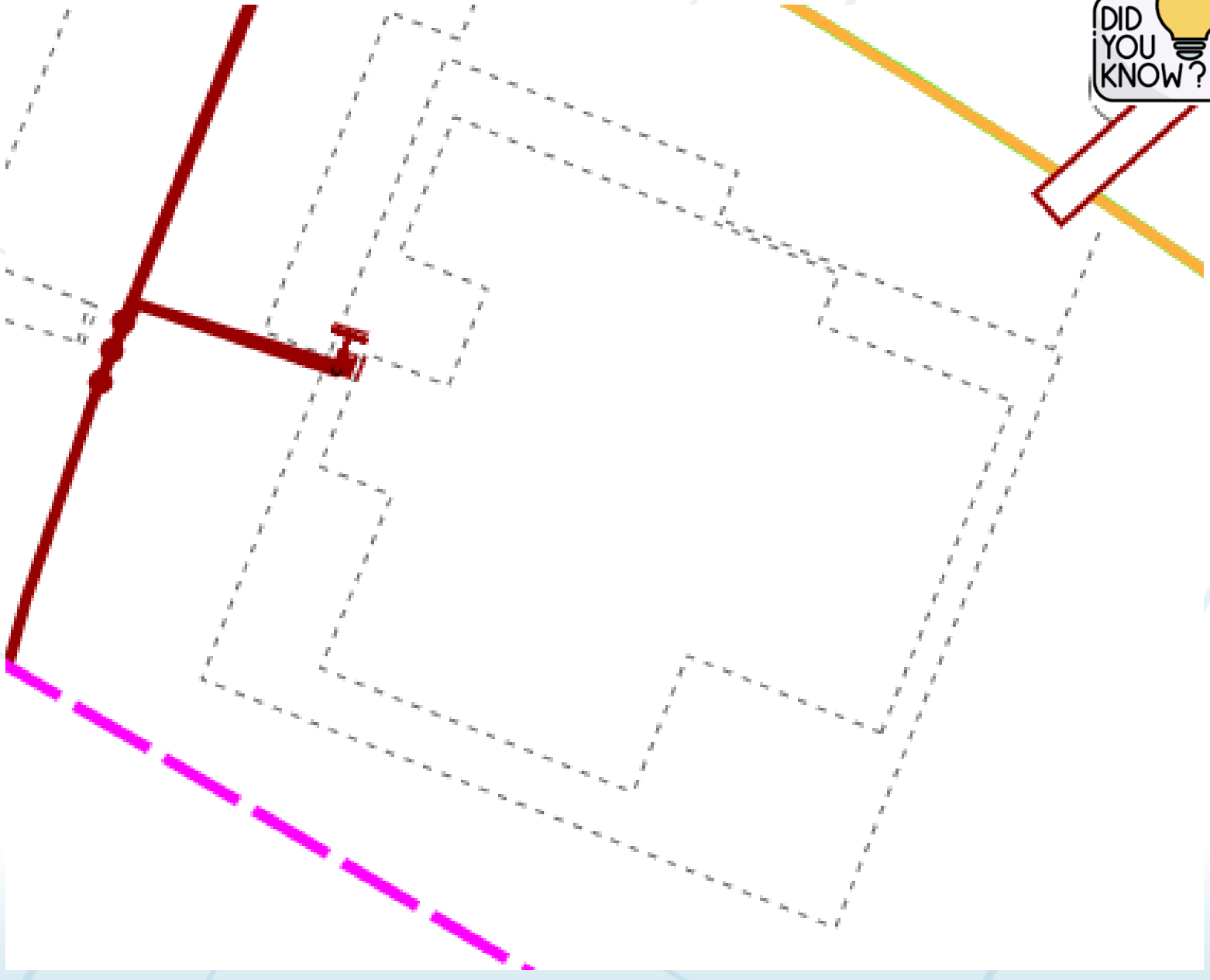

Naam	EigenTopografie
Alias	eigen topografie
Definitie	Topografie die extra wordt toegevoegd voor relatieve plaatsbepaling van objecten.
Toelichting	In principe wordt er een standaard topografische ondergrond gebruikt maar optioneel kan een eigen topografie meegeleverd worden ter nadere bepaling of oriëntatie van de ligging van een leiding of leidingelement. In geval van een geografisch object worden deze topografieën gesitueerd via het attribuut “ligging” waarbij punt, lijn en polygoon geometrieën gebruikt kunnen worden.

Extra detailinformatie

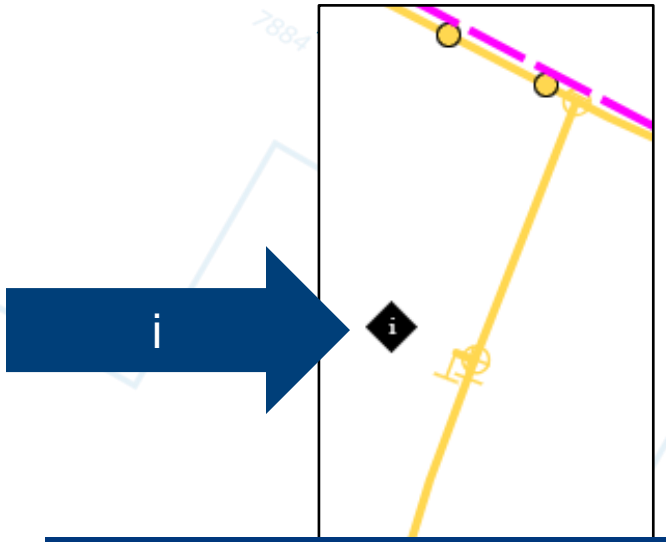

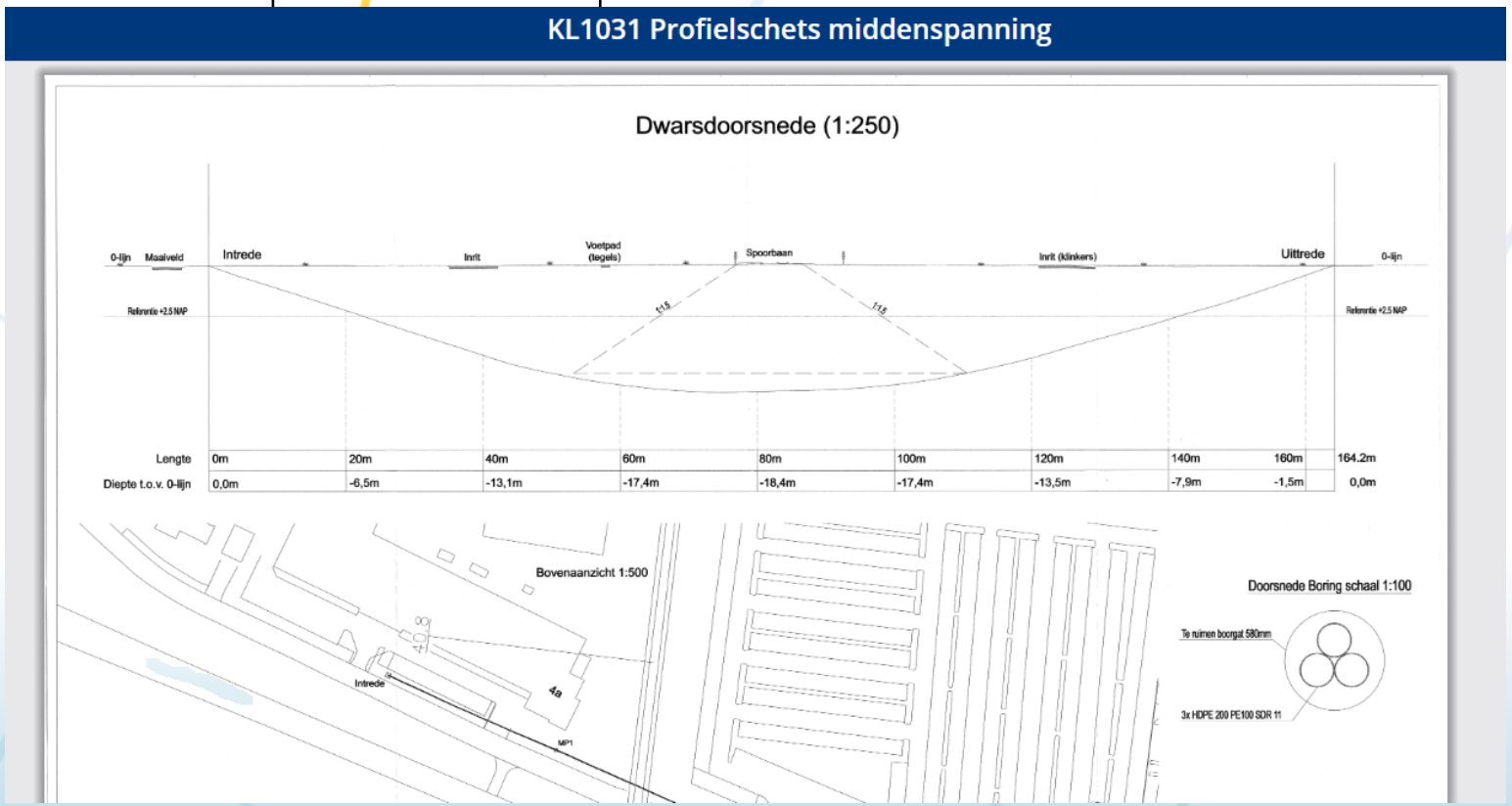

Naam	ExtraDetailinfo
Alias	extra detailinformatie
Definitie	Object dat extra informatie over één of meerdere netwerkelementen weergeeft door een verwijzing naar bestanden.
Toelichting	Het bestandstype is altijd pdf.

Extra geometrie



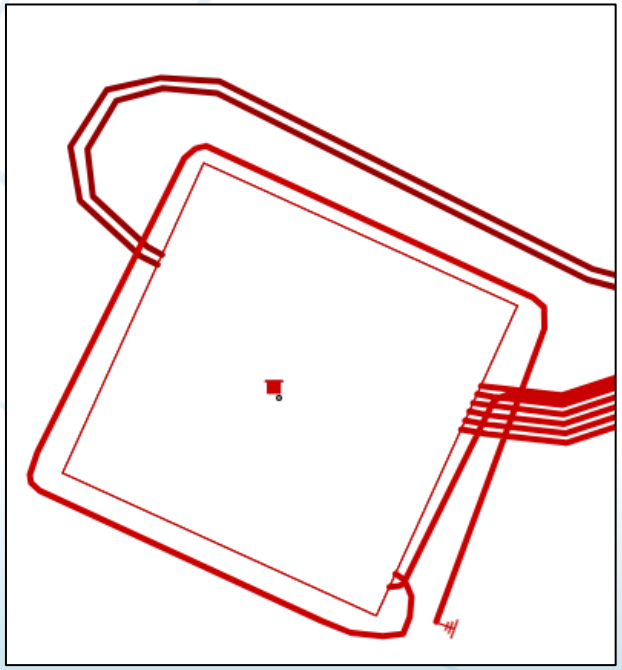

Naam	ExtraGeometrie
Alias	extra geometrie
Definitie	Verzamelobject voor extra locatie-informatie van netwerkelementen.
Toelichting	Deze klasse biedt de mogelijkheid om extra geometrie toe te voegen ten opzichte van de standaard nodes en links die onderdeel van het netwerk zijn. Dit zijn hoofdzakelijk 3D geometrieën, maar niet uitsluitend. vlakgeometrie2D biedt de mogelijkheid om een vlakrepresentatie van een netwerkelement, in 2D, op te nemen. Het is toegestaan om meerdere geometrieën op te nemen in dit object, ze sluiten elkaar niet uit.

kadaster

11:01

KLIC kalender 2026

Volgende bijeenkomsten 2026

- 19 juni 2026
- 2 oktober 2026
- 11 december 2026

Kadaster KLIC GitHub

GitHub

API management	Update	3 months ago
Aanvragen gebiedsinformatie	Update	last month
Actualiseren	update	3 years ago
BMKL	Update	4 months ago
Beheren standaarden KLIC	update	2 years ago
FAQ	update	3 years ago
Kadaster KLIC-viewer	Update	last year
Presentaties bijeenkomsten	Update	2 months ago
Synchroniseren (Rijksinspectie Digitale Infrastr...	Update	last year
Terugmelden Afwijkende Situatie	Update	5 months ago
Toepassing IMKL	Update	2 years ago
Uitleveren	Update	4 months ago
Wijzigingen	Update	2 months ago
KLIC - Geplande werkzaamheden.md	Update	yesterday

kadaster

11:01

Kadaster KLIC website

Site

Direct doen

- KLIC-melding doen
- Oriëntatieverzoek doen
- Naar KLIC-viewer
- Naar Startpagina grondroerders
- Naar Startpagina netbeheerders

Storing en onderhoud

- 0 meldingen van gepland onderhoud
- 0 gemelde storingen

Bekijk meldingen

KLIC-nieuws

Blijf eenvoudig op de hoogte van het laatste KLIC-nieuws.

- Aanmelden nieuwsbrief
- Naar KLIC nieuws
- Naar KLIC releasenotes
- Naar KLIC cijfers

Producten

- KLIC-melding
- Oriëntatieverzoek
- Calamiteitenmelding
- KLIC-viewer

Bekijk alle KLIC-producten

Documentatie

- Schademeldingsformulier
- Klantinstructie NTD actualiseren
- Klantinstructie raadplegen belangen

Bekijk KLIC-documentatie

- Bekijk technische documentatie in GitHub

Klantenservice KLIC - kabels en leidingen

Stel uw vragen over KLIC, kabels en leidingen aan onze specialisten.

0800 - 00 80 (optie 2)

naar contactformulier KLIC